Japan 2026

日本

Allt vi behöver, tacka mig sen

June –July 2026

Bīru o mittsu, onegai shimasu

Contents

1 Viktiga saker vid ankomst **2**

2 Innan vi reser, Checklist **2**

3 Landar i Narita **2**

4 Transport till Tabata (Tokyo) **3**

5 Boende information **3**

6 JR Yamanote (Gröna linjen) Master Guide **4**

7 Tokyo Områden, generaliserat **5**

8 Shopping & Tickets **5**

9 Medicin och Apotek **5**

10 Vad som är nice att alltid bära med sig **6**

11 Nödsituation **6**

12 Japanska och vart man kan behöva det **7**

13 Nightlife Survival Guide **11**

14 Tax-Free Shopping –Hur det funkar (och hur vi gör rätt) **12**

15 Backup-planer –Krismanual **13**

16 TABATA –Där vi bor **14**

17 Mount Fuji | 富士山 | 3776m **18**

18 Mt. Daibosatsu Traverse | 大菩薩嶺 | 2057m **21**

19 Mt. Oyama | 大山 | 1252m **25**

20 Mt. Hinokiboramaru | 檜洞丸 | 1601m **27**

1 Viktiga saker vid ankomst

Lagkrav: Alla utländska turister måste bära sitt fysiska pass hela tiden. Polisen kan stoppa oss random. Böter upp till 100,000 yen.

Immigration & Customs

Visit Japan Web: https://services.digital.go.jp/en/visit-japan-web/

Här kan man checka in och förbereda allt som behövs när vi ska in i landet.

Tax-Free shopping i Japan
"*When purchasing Tax-free items, instead of showing your passport or other required document, the QR Code displayed in Visit Japan Web can be shown to provide the required details to the store of purchase This is not a replacement for the user's passport, residence card or proof of immigration Note that this method cannot be used at stores where Tax-free QR Codes cannot be used, so check that the store can use QR Codes before use*"

Tax-free QR funkar i många butiker, men pass gäller alltid.
Eftersom man ändå måste ha passet på sig kanske inte detta är så relevant

2 Innan vi reser, Checklist

Måste

- Pass giltigt
- Reseförsäkring, självrisk & sjukvård
- Visit Japan Web QR
- eSIM installerad eller ha en plan klar för när vi landar
- 2 kort som fungerar (Ex. Nordea & Revolut)

Bra att ha

- Adapter (Type A/B)
- Powerbank
- Offline Google Maps

3 Landar i Narita

1. Immigration (pass + QR)
2. Baggage claim
3. Customs (QR igen)
4. Ta ut cash
5. Fixa SUICA / lägg i Apple Wallet

4 Transport till Tabata (Tokyo)

Alternativ A –Uber (35,000¥)

Bil hela vägen till boendet
Ca 35,000¥ (2000 kr (dyrt men slipper allt krångel))
Tar cirka 1 timme.
Adress: 6-chōme-4-10 Tabata, Kita City, Tokyo 114-0014

Alternativ B –N'EX + JR / Uber (3000-6000¥)

Narita Express → Tokyo Station (3000¥ / 200 kr)
N'EX är typ som ett SJ-tåg
Tar cirka 1 timme

Sen byta vid Tokyo station

Tokyo → Tabata (JR Yamanote)
Tar cirka 15 min
Eller
Uber: Tokyo → Tabata (3000¥ / 200 kr)
Adress: 6-chōme-4-10 Tabata, Kita City, Tokyo 114-0014

5 Boende information

Address: 6-chōme-4-10 Tabata, Kita City, Tokyo 114-0014
Check-in: 14 June 16:00
Check-out: 14 July 10:00

500m till Tabata Station
Närmaste konbini:

- Lawson –230m
- FamilyMart –350m
- SevenEleven –750m

Finns mer information om närliggande konbinis, restauranger, osv på rubrik 16.

Hus-Manual: https://minpakuplays2022.wixsite.com/tabata6/

Random information om regler och hur saker fungerar.

6 JR Yamanote (Gröna linjen) Master Guide

Rush hours: 07–09 • 17–19

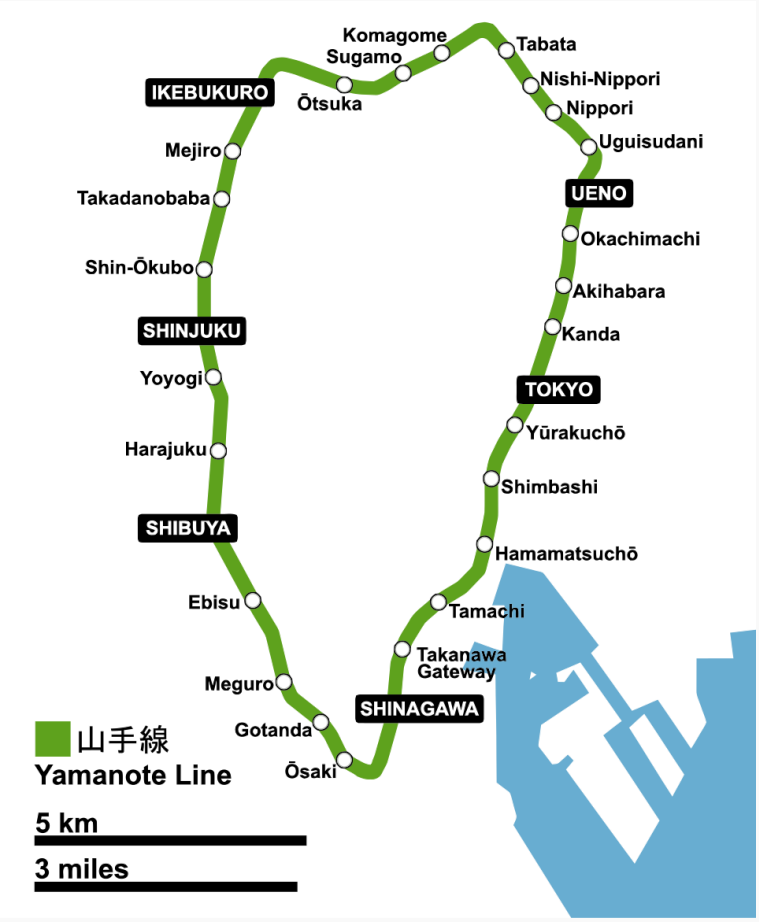

JR Yamanote Line — Alla stationer

Restider från Tabata (Vår hållplast)

Station	Riktning	Tid	Sista	Första
Ueno	Medurs mot Tokyo	10 min	01:20	04:40
Akihabara	Medurs mot Tokyo	15 min	01:15	04:40
Tokyo station	Medurs mot Tokyo	15 min	01:15	04:30
Ginza (via Yūrakuchō)	Medurs mot Tokyo	20 min	01:10	04:30
Shinagawa	Medurs mot Tokyo	30 min	00:50	04:30
Ikebukuro	Moturs mot Shinjuku	20 min	01:00	04:30
Shinjuku	Moturs mot Shinjuku	20 min	01:05	04:30
Harajuku	Moturs mot Shinjuku	25 min	01:00	04:30
Shibuya	Moturs mot Shinjuku	25 min	01:05	04:20

Party-regel: Var på stationen senast 00:45 om vi vill vara safe.
Party-regel (Alternativ): Kröka apa till 04:30.

7 Tokyo Områden, generaliserat

Asakusa: Traditionellt, Mycket Tempel, Mysigt
Shibuya: Krök / shopping / vibes
Harajuku: Caféer / shopping / fashion
Akihabara: Anime / tech
Shinjuku: Nightlife
Ikebukuro: Typ som Akihabara
Ginza: High fashion
Shimokitazawa: Vintage shops / caféer / performative
Roppongi: Massa museum / Art galleries

8 Shopping & Tickets

Biljetter: Vissa saker behöver man boka / köpa biljett. Går ofta att göra på plats.
Finns ofta hemsidor för det man vill besöka, annars:
Biljetter: https://www.klook.com/

Shibuya Sky: Den rulltrappan högt upp, säkert sett på tiktok.
Alternativ: Tokyo Metropolitan Government Building (gratis observatorium)
Tokyo SkyTree: 634 m upp i luften får man en galen vy av staden.
Placeholder: Placeholder, ställen vi vill besöka
Placeholder: Placeholder, ställen vi vill besöka
Placeholder: Placeholder, ställen vi vill besöka
Placeholder: Placeholder, ställen vi vill besöka

9 Medicin och Apotek

Benza Block (färgkodad):

- Gul: Snuva / nyser
- Silver: Ont i halsen
- Blå: Feber
- Grön: Hosta

Pabron Ace Pro-X: Funkar till typ allt.

10 Vad som är nice att alltid bära med sig

- Passet (ett måste)
- Liten väska att ha saker i
- Kontanter / plånbok
- Powerbank
- Plastpåse (finns få soptunnor)
- Servetter
- Liten fläkt (varmt)
- Sporthandduk
- Deo-wipes / body wipes
- Solkräm
- Extra tröja, om man lökar riktigt mycket någon gång
- Zip-bag för typ kamera och pass, om det blir skyfall

11 Nödsituation

Polisen: 110
Ambulans / Brandkår: 119

Närmaste polisstation (Koban): Sök "Koban"i Google Maps.
Swedish Embassy Tokyo: https://www.swedenabroad.se/en/embassies/japan-tokyo/

Mobilvarningar (Earthquake / J-Alert)

I Japan skickas nödlarm direkt till mobiltelefoner via statens varningssystem. Detta gäller även iPhones.

Kontrollera på iPhone:
Inställningar → Notiser → Government Alerts
Ska ske automatiskt om man har E-Sim i Japan.

Exempel på hur en nödsignal kan se ut

12 Japanska och vart man kan behöva det

BASFRASER

Konnichiwa	Hej
Ohayō gozaimasu	God morgon
Konbanwa	God kväll
Onegaishimasu	snälla / tack (tjänst)
Kudasai	snälla / tack (sak)
Wakarimasen	Jag förstår inte
Sumimasen	Ursäkta
Arigatou gozaimasu	Tack så mycket (presens, funkar alltid)
Arigatou gozaimashita	Tack så mycket (dåtid, när en tjänst är genomförd)
eigo ga hanasemasu ka?	Pratar du engelska (förvänta er inte många ja)
Otearai	Toalett
Hai	Ja
Iie (iie)	Nej
Un	Ja (mer casual)
Eeeh	Oj, va?
Yabai	Sjukt / galet (Kan vara positivt eller negativt)
kekkou desu	Det är lugnt
Daijoubu desu	Det är lugnt
Yokattara douzo	Om du vill, varsågod (typ om man ger upp sin plats på tunnelbanan)
Mou ichidou, itte kudasai	Kan du säga det igen
Da-me desu	Sluta med det där (när en brud kladdar på hebbe)
Sou nan desu ka?	Jaså? / Är det så?
Sou desu ne	Ja, eller hur / typ som jode
Naruhodo	Jag förstår
Sugoi	Wow
Hontō ni?	Seriöst?
Majide?	Seriöst? (Mer casual)
ii desu ne	Visst är det bra. (Lite klurig användning)
Gaman shite	eng: Be patient, endure it (kämpa)
kantan nihongo onegaishimasu	Simpel japanska tack
Nanchatte	Jag skojar bara
Joudan deshou	Du måste skämta?
Placeholderu	Placeholder

GENERELLA FRASER

Yukkuri hanashite kudasai	Kan du prata lite långsammare
Kaite moraemasu ka?	Kan du skriva det (typ på translate, dock bra med japanes-tangentbord isf)
(Watashi wa) Nihongo o benkyō shiteimasu	Jag praccar japanska
Nihongo jouzu desu ne	(Av artighet kan dom säga) Bra japanska
Svar	
Mada mada desu	Jag lär mig fortfarande
Nihongo wa mada heta desu	Min japanska är fortfarande kass
Demo ganbarimasu	Men jag försöker / ska försöka

I BUTIK (KONBINI / KASSA) VANLIGA FRASER

Irasshaimase	Välkommen (behöver inte svara i en butik)
Pointo ka-do wa omochi desuka?	Har du **poäng-kort**? (säg bara iie / daijoubu desu)
Kono mama de yoroshii desuka?	Går det bra som det är (ingen påse)
Fukuro wo owake shimasu ka?	Vill du få det i en **påse**?
Fukuro ni o-ire shimasu ka?	Vill du ha i **påse**?
Shi-ru de yoroshii deshou ka?	Går det bra med ett klistermärke? (Kan behövas om man inte tar påse)
Reshito wa yoroshii desuka?	Behöver du ett **kvitto**?
Svar	
Reshiito wa iranai desu	Kvitto behövs inte (men lika bra att ta)
Botan wo oshite kudasai	**Tryck på knappen** (Köper man öl måste man ofta trycka att man är 18+ på en skärm)

I BUTIK (KONBINI / KASSA) MINDRE VANLIGA FRASER

Shō shō **omachi** kudasai	Vänta en sekund tack
Omatase itashimashita	Tack för att du **väntade**
Otsugi no kata douzo	**Nästa** i kön, tack
O-**atatame** shimasu-ka	Vill du få det **varmt**?
Svar	
Hai, onegaishimasu	Ja, tack
Daijoubu desu	Det är lugnt
Supu-n / fo-ku / ohashi wa otsukai ni narimasu ka?	Vill du ha sked / gaffel / pinnar?
Svar	
Hai, onegaishimasu	Ja, tack
Daijoubu desu	Det är lugnt

RESTAURANG

Kādo wa tsukaemasu ka?	Tar ni kort? (betalning, inte bild)
Irasshaimase	Välkommen (svara hej om det passar, annars: se bara glad ut)
nan mei sama desu ka	Hur **många gäster** är ni?

Svar

Hitori desu	En
Futari desu	Två
San-nin desu	Tre
Yo-nin desu	Fyra

Kochira e douzo	**Den här vägen** / följ mig
Eigo no menu arimasuka?	Har ni **en engelsk meny**
Osusume arimasuka?	Har du någon **rekommendation?**
Musume arimasuka?	Har du någon **dotter?**
Kore o hitotsu onegaishimasu	**En av denna** tack (peka)
Totemo oishii desu	Det här är sjukt gott (när man äter)
Totemo oishikatta desu	Det här var sjukt gott (Efter man käkat)
Gochisousama deshita	Tack för måltiden

Bar

Kampai!	Skål!
Nani o **nomimasu** ka?	Vad **dricker** du?
Osusume wa nan desu ka?	Vad rekommenderar du?
Mou ippai?	En till?
Mō ippai kudasai	En till, tack
Chotto yopparatte imasu	Jag är lite full
Yopparatte imasu	Jag är full
Mō berobero	Jag är redan helt borta
Berobero desu	Jag är skitfull

BESTÄLLA ÖL

Toriaezu, **nama** o kudasai	Jag **börjar** med en **fatöl**
Toriaezu, **nama** o **mittsu** kudasai	Vi **börjar** med **tre** fatöl

Nama bīru kudasai	En **fat**öl tack (simpelt)
(Nama) Bīru, o **mittsu** onegai shimasu	**3** (Fat)Öl tack
(Nama) bīru o sanbai kudasai	Tre (fat)öl tack

Direktöversättningar

Exempel på direkt översättning 1: Ofta är meningsuppbyggnaden så här 1:1.

(Watashi wa)	ni juu	yon	sai desu
↑	↑	↑	↑
Jag är	20	4	år gammal

Exempel på direkt översättning 2: Lite vanligare meningsuppbyggnad (kaos).

Watashi	wa	sueden	shusshin	desu
↑	↑	↑	↑	↑
Jag	är	Sverige	ursprung	att vara

Exempel på direkt översättning 3: Destination med に (ni).

Watashi	wa	Tokyo ni	ikimasu
↑	↑	↑	↑
Jag	(ämne)	Tokyo till	åker

Exempel på direkt översättning 4: Objekt med を (o).

Watashi	wa	biiru o	nomimasu
↑	↑	↑	↑
Jag	(ämne)	öl (objekt)	dricker

Exempel på direkt översättning 5: Tid + plats före verbet (klassisk japansk struktur).

Watashitachi	wa	Hachi-ji ni	Shibuya de	aimashou
↑	↑	↑	↑	↑
Vi	(ämne)	20:00 på	Shibuya i	ses

13 Nightlife Survival Guide

Tidslogik –Hur en utekväll kan se ut
- 18–20 →Izakaya (mat + första ölen)
- 20–23 →Bar-hopping / större bar
- 23–00:30 →Klubb
- 00:45 →Sista säkra tåget (kolla Yamanote-tabellen)
- 01–04:30 →Taxi / Uber / all-nighter / karaoke till första tåget

Områden

Shibuya

- Mest energi, Yngre crowd, Många klubbar på gångavstånd, Mindre sketchy än Roppongi
- Kika Instagram: `@shibuyameltdown för en överblick`

Shinjuku

- Neon-kaos, Massa små barer och klubbar, Golden Gai (mini-barer), Bra för bar-hopping och "vi ser vad som händer"

Roppongi

- Mer internationellt, Fler turister, Dyrare, Mer scams
- Fördel: lättare att kommunicera på engelska (Behövs bara för noobs)
- Undvik folk på gatan som aktivt försöker dra in er

Missat tåget? Fördel med Karaoke

- Missar vi sista tåget →perhaps boka karaoke
- Öppet hela natten
- Ofta billigare än taxi/Uber
- AC + sittplatser + vatten (öl)

Hör detta = we out

Om någon på gatan säger:
- "Free drink", "Cheap bar", "Good girls", "My friend's bar"

→Gå vidare.

"All you can drink"är vanligt och ofta legit, men kan vara bra att kolla upp stället innan.

Golden Gai (Shinjuku)

- Små barer (5–10 platser), Vissa tar "seat charge", Gå in om dörren är öppen och det känns välkomnande
- Fråga innan vi sätter oss:

San-nin desu ga, aitemasu ka? — Vi är tre, finns det plats?

14 Tax-Free Shopping –Hur det funkar (och hur vi gör rätt)

Japan är extremt smidigt när det gäller tax-free –om man gör det korrekt.

Vad kan köpas tax-free?

Som turist (*temporary visitor*) kan vi handla utan japansk konsumtionsskatt (10%) på:

- Kläder, Elektronik, Kosmetik, Snacks, Souvenirer, Vissa apoteksvaror

Krav för att få tax-free

1. Visa pass
2. Ha "Temporary Visitor"-stämpel
3. Ta med varan ut ur Japan

Vi har redan Visit Japan Web registrerat. I många butiker kan man visa QR-koden istället för att de manuellt skannar passet. **Passet måste dock alltid bäras fysiskt.** Alla butiker accepterar inte QR-lösningen.

Minsta belopp

För att tax-free ska gälla krävs oftast:
Minst 5 000¥ i samma butik samma dag.

Hur det funkar i praktiken

- Gå till tax-free-kassan
- De skannar pass / QR-kod
- Köpet registreras digitalt
- Du betalar utan skatt (10% mindre)
- Ibland förseglas varorna i påse

Viktiga regler

Vissa varor får inte användas i Japan.
Gäller framför allt:
- Kosmetik
- Mat
- Apoteksvaror

Dessa kan förseglas i plastpåse som inte får öppnas innan avresa.
Kläder och elektronik är oftast OK att använda direkt (kolla specifika regler).
Du måste ta med varorna ut ur Japan –tullen kan i teorin kontrollera vid avresa.

15 Backup-planer –Krismanual

Vi förväntar oss inte att något händer. Men om något händer är vi redo.

Scenario 1 –Passet försvinner

Steg 1: Sök "Koban"i Google Maps (lokal polisstation). **Steg 2:** Säg att passet är borta. **Steg 3:** De hjälper oss fylla i en rapport. **Steg 4:** Få dokument (police report) –detta behövs senare.

Kontakta Svenska Ambassaden i Tokyo

Ambassaden kan:

- Utfärda provisoriskt pass, Ge instruktioner, Hjälpa vid identitetsverifiering

Ha redo:

- Passkopia (digital)
- ID och personnummer
- Polisrapport

Scenario 2 –Jordbävning

Japan har jordbävningar. De flesta är små.

Om vi är inomhus:

- Stå inte i dörröppning
- Skydda huvudet
- Håll oss borta från fönster

Om vi är utomhus:

- Gå bort från byggnader, undvik glasfasader
- Skakningar brukar vara korta

Efter skakning: Följ lokal information och personalens instruktioner.

Scenario 3 –Vi tappar bort varandra

Tokyo är stort. Telefoner kan dö.

Regel: Bestäm en backup-plats i varje område.

Exempel:

- "Tappar vi varandra i Shibuya → möts vid Hachiko."
- "I Skytree-området → möts vid huvudentrén."

Bestäm även:

- Tid att vänta (ex. 20 min)
- Vad man gör om ingen dyker upp

16 TABATA –Där vi bor

Mini-karta (översikt)

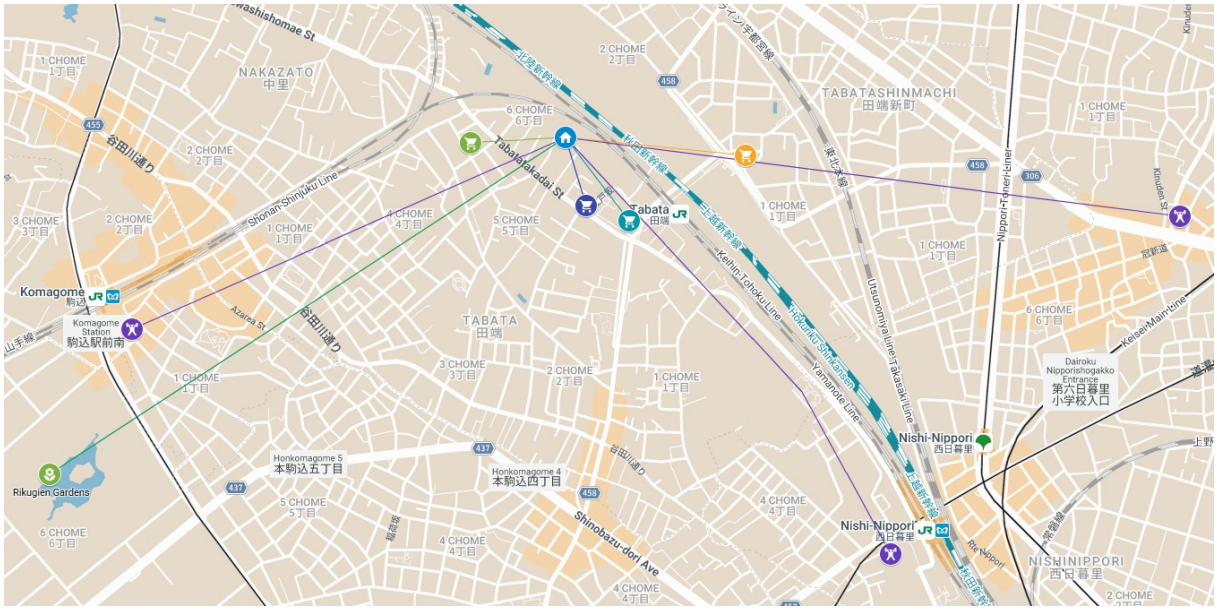

• Rikugien Gardens | • Lawson | • FamilyMart | • SevenEleven | • Supermarket | • Gym

Gym –Anytime Fitness (24/7)

Alternativ nära oss:

- **1.2 km - Anytime Fitness Komagome** | Den vänstra på kartan
  〒 170-0003 Tokyo, Toshima City, Komagome, 1 Chome–38–2 渋谷ＴＲビル 3F
- **1.4 km - Anytime Fitness Nishi-Nippori** | Den nedersta på kartan
  〒 116-0013 Tokyo, Arakawa City, Nishinippori, 3 Chome–6–14 マンション道灌山 201 号室
- **1.8 km - Anytime Fitness Shinmikawashima** | Den högra på kartan
  〒 116-0012 Tokyo, Arakawa City, Higashiogu, 1 Chome–1–4 小澤第一ビル 2F

Medlemskap

- 1-månads medlemskap möjligt — (Startavgift kan förekomma)

Kräver oftast:

- Pass | Japansk adress (boendet funkar) | Ibland japanskt bankkonto (autogiro)

> Många japanska Anytime kräver japanskt bankkonto för autogiro. Det kan bli krångligt.

Day Pass (om tillgängligt)

- 2 000–3 500¥ per gång • Betalas på plats • Kräver pass

Alla Anytime i Japan erbjuder inte day pass. Vi får maila / ringa i förväg, eller gå dit och fråga

Gymregler (Typ samma som Sverige)

- Inga ytterskor på träningsgolvet — Handduk på maskiner — Rengör efter dig — Skrik inte

Mat i området

Konbini inom 10 minuter

- **230 m - Lawson Tabata** | Blå på kartan
  Japan, 〒 114-0014 Tokyo, Kita City, Tabata, 6 Chome−3−1 スターハイツ

- **260 m - Maruetsu Petit Tabata Shop** | Grön på kartan
  5 Chome-13-13 Tabata, Kita City, Tokyo 114-0014, Japan

- **350 m - FamilyMart Tabata Station** | Turkos på kartan
  Japan, 〒 114-0014 Tokyo, Kita City, Tabata, 6 Chome−1−1 アスカタワ

- **750 m - 7-ELEVEN Kita Ward Tabata Station** | Orange på kartan
  1 Chome-13-2 Higashitabata, Kita City, Tokyo 114-0013, Japan

Restauranger i närheten

(Har endast testat Yakitori och Kura, men hittade några som såg trevliga ut)

- **750 m - Annon | 和亭安穏**
  Japan, 〒 114-0014 Tokyo, Kita City, Tabata, 3 Chome−3−11 天野ビル 1F
  "*Now that's what I call a restaurant. Lunch worth around 2000¥ for half of the price, vegetables, soup that actually tastes like something made by a human. Excellent stuff, and the shop is very stylish to boot. Looks like fun in the evening too, I'll definitely come back.*"

- **850 m - Beard | ビアド**
  2 Chome-9-1 Higashitabata, Kita City, Tokyo 114-0013, Japan
  "This is one of the restaurants recommended by Tabata locals. The staff are friendly and kind, and the atmosphere is such that you'll want to return once you've been there. The beer and pizza here are recommended."

- **1.1 km - タバタ食堂千魚**
  Japan, 〒 114-0012 Tokyo, Kita City, Tabatashinmachi, 2 Chome−1−13 Yuminaga Bldg, 1F
  "Excellent food and service", "*It's a little far from the station, but it's well worth the trip!"*

- **1.3 km - YAKITORI Torikizoku Komagome | 鳥貴族駒込店**
  Japan, 〒 170-0003 Tokyo, Toshima City, Komagome, 1 Chome−43−11 2F
  "*Galen rekommendation, billiga smårätter och megabeers. Boka bord online*"*- Elliot*
  "As a foreigner the chicken was absolutely excellent as was the cabbage and the pork belly and steak. Loved it so much."

- **2.5 km - Kura Sushi | くら寿司フレスポ東日暮里店**
  Japan, 〒 116-0014 Tokyo, Arakawa City, Higashinippori, 6 Chome−2−14 フレスポ東日暮里 3F
  "*Galen rekommendation, sushi och öl som serveras på band. Boka bord online*"*- Elliot*
  "*Literally in love with everything in this place. The food was amazing I give it a 10/10 I went there like 3 times the same week*""*Fun to experience conveyer belt sushi, although we mainly ordered through the tablet. Not many tourists*"

Parker & Promenader

- **1.3 km - Rikugien Gardens** | Grön på kartan (till vänster)
  6 Chome-16-3 Honkomagome, Bunkyo City, Tokyo 113-0021, Japan
  The Rikugien Gardens were created around 1700 as a strolling garden, at the request of Japan's fifth shogun, Tsunayoshi Tokugawa (1646–1709). The quiet grounds depict 88 scenic spots that are in Kishu Wakanoura and from Japanese poems, and offer beautiful views from every angle. Relax in one of the three tea houses with views of the central pond, and forget for a moment that you are in modern Tokyo

- **3.2 km - Ueno Park** | Kaneiji Temple ligger även precis bredvid
  Uenokoen, Taito City, Tokyo 110-0007, Japan
  Ueno Park (上野公園, Ueno Kōen) is a large public park next to Ueno Station in central Tokyo. The park grounds were originally part of Kaneiji Temple, which used to be one of the city's largest and wealthiest temples and a family temple of the ruling Tokugawa clan during the Edo Period.
  Today Ueno Park is famous for the many museums found on its grounds, especially the Tokyo National Museum, the National Museum for Western Art, the Tokyo Metropolitan Art Museum and the National Science Museum. It is also home to Ueno Zoo, Japan's first zoological garden.

- **2.2 km - Asukayama Park**
  〒 114-0002 Tokyo, Kita City, Ōji, 1-chōme−1−3 飛鳥山博物館, Japan
  The park is a relaxing spot to escape from the surrounding concrete jungle. It also has the Asukayama Park Monorail—probably the shortest, slowest, and smallest passenger monorail in the world. The free journey between the bottom and top stations takes less than two minutes.

Tempel & Kultur

- **2.5 km - Kaneiji Temple 寛永寺**
  Kanei-ji Reien, 7 Chome-1 Yanaka, Taito City, Tokyo 110-0001, Japan
  Kaneiji is a Buddhist temple located in a residential neighborhood on the outer edge of Ueno Park in Tokyo. Six of 13 of the Tokugawa clan who became shogun are buried in the temple's graveyard.
  Built in 1625, the temple had Tokugawa clan support from the beginning. In fact, its land was donated by Tokugawa Hidetaka, the third son of Ieyasu and the second shogun. The temple continued to be an important funeral temple, which is why six of the Tokugawa clan's leaders are buried here.
  The bronze statue of Saigo Takamori in Ueno Park is one of the most famous objects in Japan. One of the leaders of the rebellion supporting the Emperor, he was the leader of the Satsuma clan from Kagoshima, a key part of the Imperial forces.
  During the Battle of Ueno, the Satsuma troops attacked the main gate of the temple head-on. They suffered tremendous casualties, but this bold move helped end the conflict quickly. Saigo's statue is near the main entrance to the park, almost on the opposite end from Kaneiji.

Finns i Rise of the Ronin spelet, fränt:
https://rise-of-the-ronin.fandom.com/wiki/Kaneiji_Temple



17 Mount Fuji | 富士山 | 3776m

Mount Fuji är Japans mest ikoniska berg och ett heligt landmärke. Över 200 000 personer bestiger berget varje år. Det är populärt –men ska tas seriöst.

Climbing Season & Regler

- **Officiell säsong:** Början av juli –10 september
- **Yoshida Trail:** 1 juli –10 september
- **Övriga trails:** 10 juli –10 september
- **Avgift 2025:** 4000¥ (obligatorisk, alla trails)
- Online-reservation krävs

Trailheads är stängda mellan **14:00–03:00**. Endast vandrare med stugbokning får **starta** under detta spann. Syftet är att stoppa "bullet climbing".

De fyra lederna (översikt i text)

Yoshida Trail (2 300 m) 5–7h upp • 3–5h ner • Daglig gräns: 4000 personer • Mest populär • Flest stugor • Separat upp- och nerled • Soluppgången sker på denna sida.

Subashiri Trail (2 000 m) 5–8h upp • 3–5h ner • Ingen daglig gräns • Mindre trång i början, möter Yoshida runt 8:e stationen.

Gotemba Trail (1 400 m) 7–10h upp • 3–6h ner • Ingen daglig gräns • Längst och mest fysiskt krävande.

Fujinomiya Trail (2 400 m) 4–7h upp • 2–4h ner • Ingen daglig gräns • Kortast väg till toppen. Mest direkt.

5th Station

Upp till 5th Station finns det ordentliga vägar. Här finns:

- Toaletter • Butiker • Information center • Uthyrning av utrustning (Hjälm om man vill)

Buss från Tokyo (Shinjuku):

- 3800¥ enkel • Ca 150 minuter • Går varje timme under säsong

Exempel: Start 04:00 (utan övernattning)

04:00 — Start från 5th Station | **10:00–13:00** — Topp | **14:00** — Nedstigning | **18:00–21:00** — Tillbaka vid 5th Station

---

Bullet climbing (utan vila) är egentligen inte rekommenderat. MEN, lugnt tempo, dricka vatten, korta pauser, så ska vi se till att lösa det.

Utrustning

- Riktiga vandringskängor
- Bra jacka (kan vara under 0° på toppen)
- Regnkläder / Lager som skyddar från regn
- Vantar kan vara skönt högre upp
- Pannlampa (Beroende på start)
- Tillräckligt med vatten
- Kontanter (kort accepteras ofta ej)
- Stavar kan vara nice

Bergsstugor

Pris: 10 000–16 000¥ per natt (inkl. mat) Bokning öppnar: 1 april Kort accepteras ofta inte. Små stugor endast för att vila, delas med många andra. (Finns inte rinnande vatten)

Boka: https://mtfuji.jpn.org/availablelist.php

Crowds & När är det bäst att gå?

Climbing Mount Fuji är extremt populärt –både bland japaner och internationella besökare. Högsäsongen infaller under de japanska skolloven, ungefär **20 juli –slutet av augusti**.

> Att undvika alla människor är nästan omöjligt –men en del av upplevelsen är gemenskapen. Att gå upp tillsammans med andra från hela världen är en unik del av Fuji-upplevelsen.

Bästa balansen:

- Vardagar
- Första halvan av juli
- Innan skolloven börjar

Nackdelen med tidig juli är att vädret kan vara mer instabilt än senare under säsongen.

Reservation & Bokning

> Online-reservation krävs innan man passerar trail-gaten. Avgift: **4000¥ per person**

Yoshida Trail:
https://www.asoview.com/channel/tickets/r0Gpg8xllI/

Subashiri, Gotemba & Fujinomiya:
https://fujisan223registration.com/2025/en.html

Känns Mount Fuji som en för stor utmaning?
Det finns fler alternativ. Trots att jag tycker det är lite mesigt kan vi välja något annat berg.

Nedan kommer jag kort presentera olika berg som jag har scoutat ut.

Bra hemsida med information om Japanska berg:
https://en.culmina.jp/kanto/hinokiboramaru

18 Mt. Daibosatsu Traverse | 大菩薩嶺 | 2057m

Utsikt mot Mt. Fuji från Daibosatsu-ridgen

Område: Chichibu-Tama-Kai National Park, Yamanashi
Start & Slut: Kaminikkawa-tōge (上日川峠)
Högsta punkt: 2 057 m (Mt. Daibosatsu)
Start-höjd: 1 600 m
Distans: 4–14 km (beroende på hur långt vi fortsätter på ridgen)
Tid: 3–7 h (flexibel loop)
Svårighet: Enkel (mycker enklare än Galdhøpiggen)

Detta är en av de bästa panoramavandringarna nära Tokyo. Man får utsikt mot Fuji **under själva vandringen** — inte bara från toppen.

Den stora fördelen här är att rutten är **flexibel**. Vi kan göra en kort och säker tur (topp + tillbaka), eller bygga på med mer ridgeline om allt känns bra och tiden finns.

Hur ser det ut på plats?

Startpunkt: Kaminikkawa-tōge (上日川峠)

Vid trailhead finns:

- Toaletter • Parkering och vändplats för buss • Tydliga skyltar mot **Daibosatsu** och ridgen

Som jag tolkar det är det inte ett stort visitor center, men trailhead är en etablerad bergsstart och känns **organiserad** även för en dum svensk.

Vatten: Det finns inga säkra vattenstationer längs ridgen. Ta med **2–3 liter per person** (mer om det är varmt), samt snacks/lunch.

Terräng & Upplevelse

- Start i skog och stadig stigning upp mot ridgen | Öppnare partier med bred utsikt (Fuji vid klart väder) |Mt. Daibosatsurei (2 057 m) som "main summit"| Lång ridgeline (känns som mini-alpin vandring)

Stigen är **tekniskt enkel** (ingen klättring), men det är fortfarande bergsterräng, så det blir en rolig upplevelse. Liknande med berg i Norge, men utan snö.

Flex Loop Strategy –Vad menar jag?

Höjdprofilen visar tydligt att högsta punkten nås redan cirka **2 km från start**. Det betyder att vi är **garanterade att nå toppen** även om ni vill ta det extremt säkert tidsmässigt. Ingen risk att missa toppen för att hinna med en buss.

Höjdprofil: högsta punkt tidigt, därefter lång ridgeline och längre nedstigning

Detta innebär:

- **Toppen snabbt:** ca 60–90 minuter i lugnt tempo
- **Ridge walking:** resten är lång och panoramisk ridgeline
- **Full kontroll:** vi kan vända när som helst och ändå få "main payoff"

Det är inte en "allt eller inget"-tur. Ni väljer själva:

- **Plan A (säkrast):** Daibosatsu (topp) + samma väg tillbaka
- **Plan B:** Fortsätt 1–2 timmar längs ridgen och vänd
- **Plan C:** Gör en längre loop/ridge-variant om väder, tempo och bussar tillåter

> **Nyckelidén med alternativet:** Eftersom toppen nås tidigt kan vi "nå målet"snabbt, för att sedan bara fortsätta så länge vi vill och njuta.

Transport –Komplett och Säker Plan (Början av Juli)

Detta är en plan för en dagstur med marginaler inbyggda. Den måste justeras / kontrolleras när det närmar sig och tidtabeller publiceras. Planen bygger på att ta **08:10-bussen** från Kai-Yamato.

Total restid enkel väg: 2.5–3 timmar
Total dagslängd: 13–14 timmar dörr till dörr

Detaljerad Tidsplan (Med Marginal)

Tid	Moment
05:45	Lämna boendet i Tabata
06:00	JR Yamanote Line → Shinjuku (går var 3–5 minut)
06:30	JR Chūō Rapid → Otsuki
07:45	Ankomst Otsuki
07:55	JR Chūō Main Line (Local) → Kai-Yamato
08:10	Ankomst Kai-Yamato (10–15 min buffert innan buss)
08:10	Eiwa Kotsu Bus → Kaminikkawa-tōge
08:50	Ankomst trailhead
09:00	Start vandring
10:00–10:30	Trolig ankomst Daibosatsurei (toppen)
12:30	Senaste rekommenderade vändtid
14:30–15:00	Tillbaka vid Kaminikkawa-tōge
15:45	Buss tillbaka till Kai-Yamato
16:30–17:00	Tåg mot Otsuki → Shinjuku
19:30–20:00	Tillbaka i Tokyo

Varför vändtid 12:30? Då har vi fortfarande god marginal att gå tillbaka även om tempot är långsamt, vi kan ta längre pauser, eller om vädret blir sämre.

Biljetter –Hur köper man?

JR-tåg (Yamanote + Chūō)

- Det är JR (samma som gröna linjen) Använd Suica (blippa in/ut) | Ingen bokning krävs för **Rapid** (中央線快速) | Limited Express går snabbare men kräver extra biljett (undvik för enkelhet) | Ungefärlig kostnad Tokyo → Kai-Yamato: 2 000–2 500 ¥.

Eiwa Kotsu buss

- Betalas ombord | Ca 1 000–1 200 ¥ enkel väg | Kontanter rekommenderas (tror inte detta är fallet längre) | IC-kort (SUICA) fungerade när jag åkte buss | Ingen förbokning krävs

Tåglinjer –Exakta linjer

1) Tabata → Shinjuku (JR Yamanote)
Ca 20 min, går mycket ofta.

2) Shinjuku → Otsuki (JR Chūō Line Rapid)
Ca 70 min. Avgår ofta var 10–20 minut på morgonen.

3) Otsuki → Kai-Yamato (JR Chūō Main Line, Local)
Ca 20 min. Det är ett enkelt byte i Otsuki. Stationer och skyltar är tydliga på engelska.

Buss –Vanliga tider i säsong

Eiwa Kotsu 大菩薩上日川峠線 (mitten april – november)

Vanliga avgångar dit (morgon):

- 08:10 • 09:20 • 09:50

Vanliga returer (eftermiddag):

- 14:00 • 15:00 • 15:45

Målet är att planera för 15:00 eller 15:45-bussen, med marginal.

Backup om vi blir sena

Om ni missar bussen (Ska inte hända):

- Taxi till Kai-Yamato tar ca 40–50 min (beroende på trafik)
- Kostnad: ca 10 000–15 000 ¥
- Uber är **inte** pålitligt i området (taxi är mer realistiskt)

Säkerhetsregel: Om vädret blir dåligt eller vi känner oss sega — kör Plan A (topp + tillbaka) och ta en tidigare buss hem.

Utrustning (dagstur)

- Vandringskängor (eller stabila trail-skor)
- 2–3 L vatten
- Lunch + snacks (energi)
- Regnjacka / vindjacka
- Solskydd + hatt
- Offline-karta (t.ex. YAMAP/AllTrails) + powerbank

Fördelar

- Start och slut på samma plats (ingen "point-to-point"stress)
- Toppen nås tidigt (vi får payoff direkt)
- Vi kan vända när som helst
- JR-tåg hem går hela kvällen
- Taxi är en realistisk backup om något går fel (men bör undvikas!)

Detta gör Mt. Daibosatsu till en av de mest balanserade och genomförbara bergsdagarna nära Tokyo i början av juli.

19 Mt. Oyama | 大山 | 1252m

Område: Tanzawa-Ōyama Quasi-National Park (Kanagawa)

Högsta punkt: 1 252 m

Tid: ca 4–6 h vandring
(beroende på väg + pauser)

Stigning: ca 900–950 m
(om man går mestadels till fots)

Svårighet: Lätt
(tekniskt enkel, men brant på sina ställen)

Fördelar:
Fuji-utsikt + shrine + turistvänlig logistik + mycket enklare än ex. Galdhøpiggen
Nackdelar:
Mycket enklare än ex. Galdhøpiggen. Inte så spännande, mindre fokus på berget och mer som en liten vandring

Mt. Ōyama är ett av de mest turistvänliga "riktiga bergen"nära Tokyo. Det är ett **mycket enklare alternativ till Fuji** om vi vill ha en bergsdag med **utsikt mot Fuji när vädret är klart**. Till skillnad från Fuji behövs **ingen reservation**, ingen gate och vi kan alltid vända utan att det blir krångel.

Varför Ōyama är ett bra alternativ

- **Enkel transport:** Odakyu-tåg + buss (och valfri cable cart).
- **Flexibel dag:** Vi kan göra den kort eller längre utan stress.
- **Kultur på vägen:** Afuri Shrine + klassisk pilgrims-vibe.
- **Turistvänligt:** Många andra vandrare, skyltat, service i området.

Två sätt att göra turen

A) Normal: Buss till Oyama Cable →gå upp via pilgrimsleden →ner via samma väg.
B) "Cable-assist": Ta cable cart upp (sparar ben) →topp →gå ner. (Galen mes-varning på den)

Poängen: Ōyama är **enkelt.** Utan större ansträngning kan vi få en cool dag (shrine + utsikt + bergskänsla).

Hur ser det ut på plats? (service, skyltning, vatten)

Startområde (Oyama Cable bus stop / trail-entré):

- "Koma-sandō"(shopping street) upp mot berget med mat/snacks.
- Tydlig "hiking-vibe"och mycket folk på helger.
- Skyltning mot **Afuri Shrine** och vidare mot toppen.

Informationskänsla: Det är inte ett "nationalpark visitor center"i Fuji-stil, men Ōyama är **välorganiserat och lätt att följa** p.g.a. många besökare och tydliga leder.

Vatten & pauser: Vi kommer hitta kiosker/shops i basområdet och ofta möjlighet att köpa dryck på vägen upp mot shrine. Uppe på ridgen/toppdelen borde vi däremot **inte** räkna med regelbundna vattenstationer. **1.5–2.5 L per person.**

Transport –Plan (början av juli)

Grundlogik:

- **Odakyu Line:** Shinjuku →Isehara (ca 60 min)
- **Kanachu-buss:** Isehara →"Oyama Cable"(ca 25–30 min)
- **Valfritt: Oyama Cable Car** upp mot shrine-nivå (Mesigt)

Turistvänlig biljett-logik:
Tåg: Suica/PASMO (Blippa).
Buss: Ofta funkar Suica/PASMO, annars kontanter.
Freepass (paket): "Tanzawa–Ōyama Freepass"kan köpas digitalt (endast värt om man ska åka cable cart).

Tidsplan –"Säker dag"(tabell)

Tid	Plan
07:00	Lämna Tabata (JR Yamanote mot Shinjuku)
07:25	Ankomst Shinjuku, byt till Odakyu
07:40	Odakyu: Shinjuku →Isehara (sikta på "nästa bra"avgång)
08:40	Isehara: buss mot "Oyama Cable"
09:10	Framme vid Oyama Cable bus stop, starta vandring
10:30	Afuri Shrine-området / lång paus / foton
12:00	Topp (om vi kör "normal pace")
13:00	Börja nedstigning (ger mycket marginal)
15:30–16:30	Tillbaka vid basområdet, mat/snacks, buss tillbaka
17:30–18:30	Tillbaka i Shinjuku
19:00	Tillbaka i Tabata

Den här planen är bara ett exempel och för att vi ska ha **marginaler**. Vi kan starta tidigare om vi vill ha max Fuji-sikt (morgon = bäst chans) + mindre folk.

20 Mt. Hinokiboramaru | 檜洞丸 | 1601m

Område: Tanzawa Mountains (Kanagawa)
Högsta punkt: 1 601 m
Start & Slut: Nishi-Tanzawa Visitor Center (西丹沢ビジターセンター)
Rutt: Tsutsuji Shindō Trail (rundtur / out-and-back)
Tid: ca 6–8 h effektiv vandring (beroende på pauser)
Stigning: ca 1 000 m (fysiskt krävande)
Svårighet: Medel (tekniskt enkel, men lång och brant på sina ställen)

Hinokiboramaru är en av de mest uppskattade "riktiga" dagsturerna i västra Tanzawa. Till skillnad från mer turistiska berg (som Oyama) känns detta mer som **skog + dalgång + bergsvandring**, och mindre promenad. Starten vid **Nishi-Tanzawa Visitor Center** gör också logistiken enklare.

Hur ser det ut på plats? (Startpunkten)

Nishi-Tanzawa Visitor Center är den klassiska basen för hikes i området. Här finns:

- Toaletter | Karta/skyltning och grundinfo om leder | Parkering och tydlig trailhead-känsla

Det är inte som Fuji, men det är en etablerad startpunkt där många vandrare börjar/slutar.

Vatten: Räkna inte med säkra refill-stationer uppe på berget. Ta **minst 2 L** (helst 2.5–3 L om det är varmt), plus salter/snacks. Bäckar kan förekomma (men vet ej hur rent vatten),

Terräng & upplevelse

- **Start i dal/skog:** jämn stigning, mycket grönt
- **Längre upp:** mer ås/rygg-känsla och öppnare partier
- **Mot toppen:** luftigare miljö, ofta bra utsikt vid klart väder

Den är **tekniskt enkel att gå** (ingen klättring), men **fysiskt krävande** eftersom det är lång dag med mycket höjdmetrar.

Transport (Tokyo → trailhead) –steg för steg

Steg 1: Tabata → Shinjuku

- JR Yamanote Line (går ofta, ingen planering behövs)

Steg 2: Shinjuku → Shin-Matsuda

- Odakyu Line till **Shin-Matsuda**
- Använd IC-kort (SUICA)

Steg 3: Shin-Matsuda → Nishi-Tanzawa Visitor Center

- Buss opererad av Fujikyu (Fujikyu Shonan / Fujikyu Mobility beroende på benämning)
- Detta är **sista hållplatsen** för många hikes i västra Tanzawa

Bussar (viktigaste delen att checka i Juli)

Bussar går **inte supertätt**, och tider skiljer ofta på vardag vs helg/säsong. Som exempel visar publicerade tidtabeller/transfer-sidor avgångar i stil med:

- **Shin-Matsuda mot Visitor Center:** runt **08-tiden** & **09-tiden** samt några efter lunch
- **Retur från Visitor Center mot Shin-Matsuda:** eftermiddag (t.ex. kring **14:40** och **15:40** i vissa upplägg)

Dagsplan (exempel)

Tid	Plan
05:30	Lämna Tabata (marginal + enklare om något strular)
06:00	JR Yamanote: Tabata → Shinjuku
06:30	Odakyu: Shinjuku → Shin-Matsuda
07:45	På plats vid busshållplats, köpa ev. biljett / ställa frågor
08:xx	Buss: Shin-Matsuda → Nishi-Tanzawa Visitor Center
09:3x	Start vandring
12:30	"Status-check": energi + tempo + väder (bestäm om ni fortsätter mot toppen)
14:00–16:30	Målfönster för att vara tillbaka vid Visitor Center (beroende på vald returbuss)
16:xx–17:xx	Buss tillbaka till Shin-Matsuda
Kväll	Tåg tillbaka till Tokyo

Upplägg: välj **returbuss** först och planera vandringen runt den. Hinokiboramaru är out-and-back, så "vänd när som helst" funkar.

Varför välja denna?

- En av de mest "bergiga" dagsturerna nära Tokyo (utan Fuji-folkmassa)
- Out-and-back gör den **enkel att vända** om vi vill hinna buss med stor marginal
- Start vid etablerad trailhead (Visitor Center) gör logistik och orientering enklare